ELEV 2866 ft MSL
873 m MSL

HÜTTEN-HOTZENWALD
EDSF

FIS
LANGEN INFORMATION 128.950
ZÜRICH INFORMATION 124.700

HOTZENWALD RADIO
125.815 Ge (15 NM 3000 ft GND)

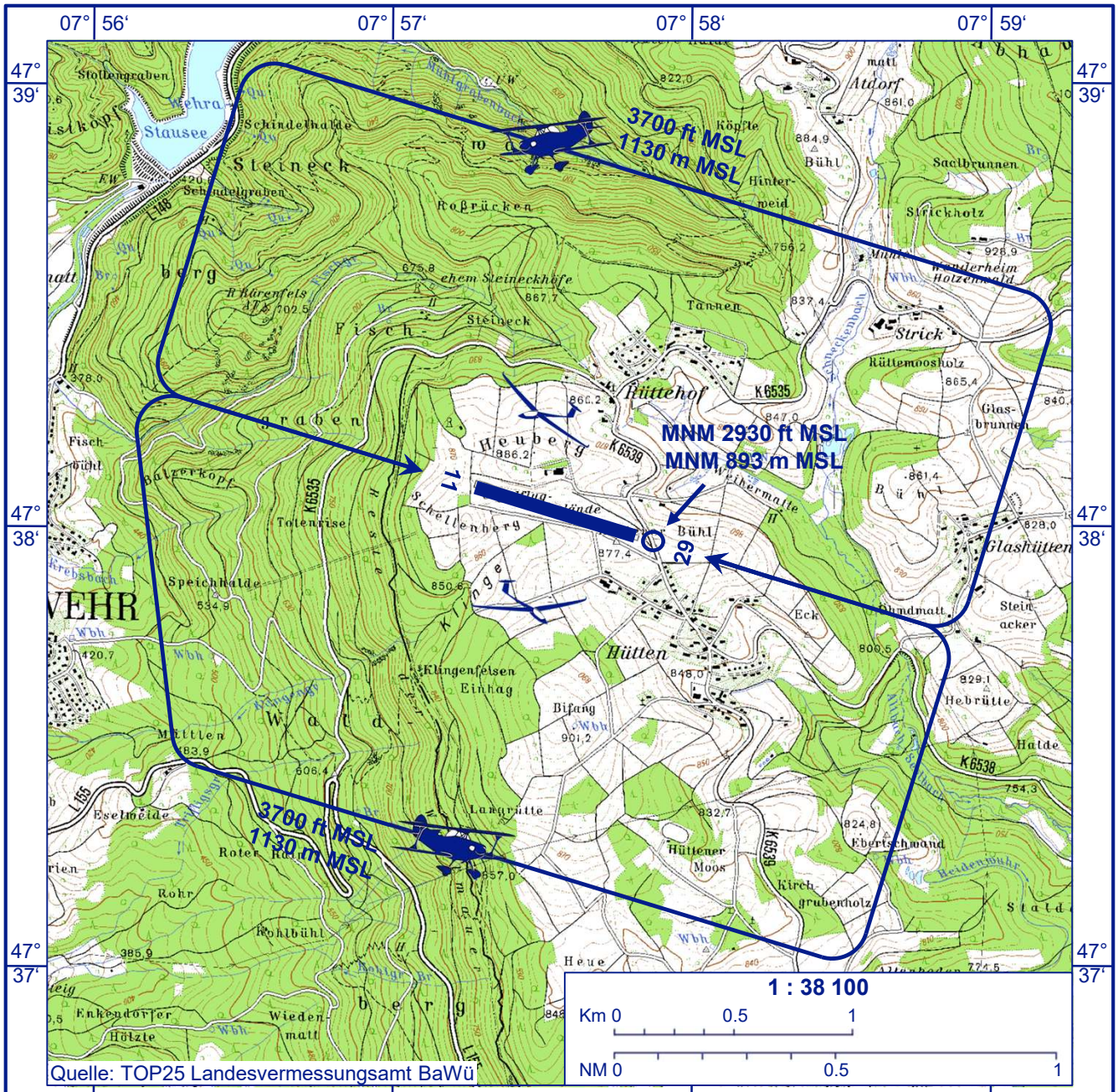

Quelle: TOP25 Landesvermessungsamt BaWü

Contact HOTZENWALD RADIO at least 5 MIN prior reaching the AD.
TKOF/LDG of powered ACFT are not permitted as long as the yellow flashing warning light on the glider whinch is turned on.
Avoid residential areas in the vicinity of AD.
Look out for gliders.
High voltage power line east of AD.
Steep hillside west of the runway threshold 11, turbulences may occur.
The street east of the AD must be overflown in min. 45 ft (15 m) ground, MNM 2930 ft MSL .

HOTZENWALD RADIO spätestens 5 MIN vor Erreichen des Platzes rufen.
Das Starten und Landen von motorgetriebenen LFZ ist nicht gestattet, solange die gelbe Warnblinkleuchte auf der Startwinde in Betrieb ist.
Das Überfliegen von Wohngebieten in Flugplatznähe ist zu vermeiden.
Auf Segelflüge achten.
Hochspannungsleitung östlich des Platzes.
Steil abfallender Hang westlich der Schwelle 11, bei Wind aus Ost mit Lee rechnen.
Die Straße östlich des Flugplatzes in min. 45 ft (15 m) überfliegen, MNM 2930 ft MSL.

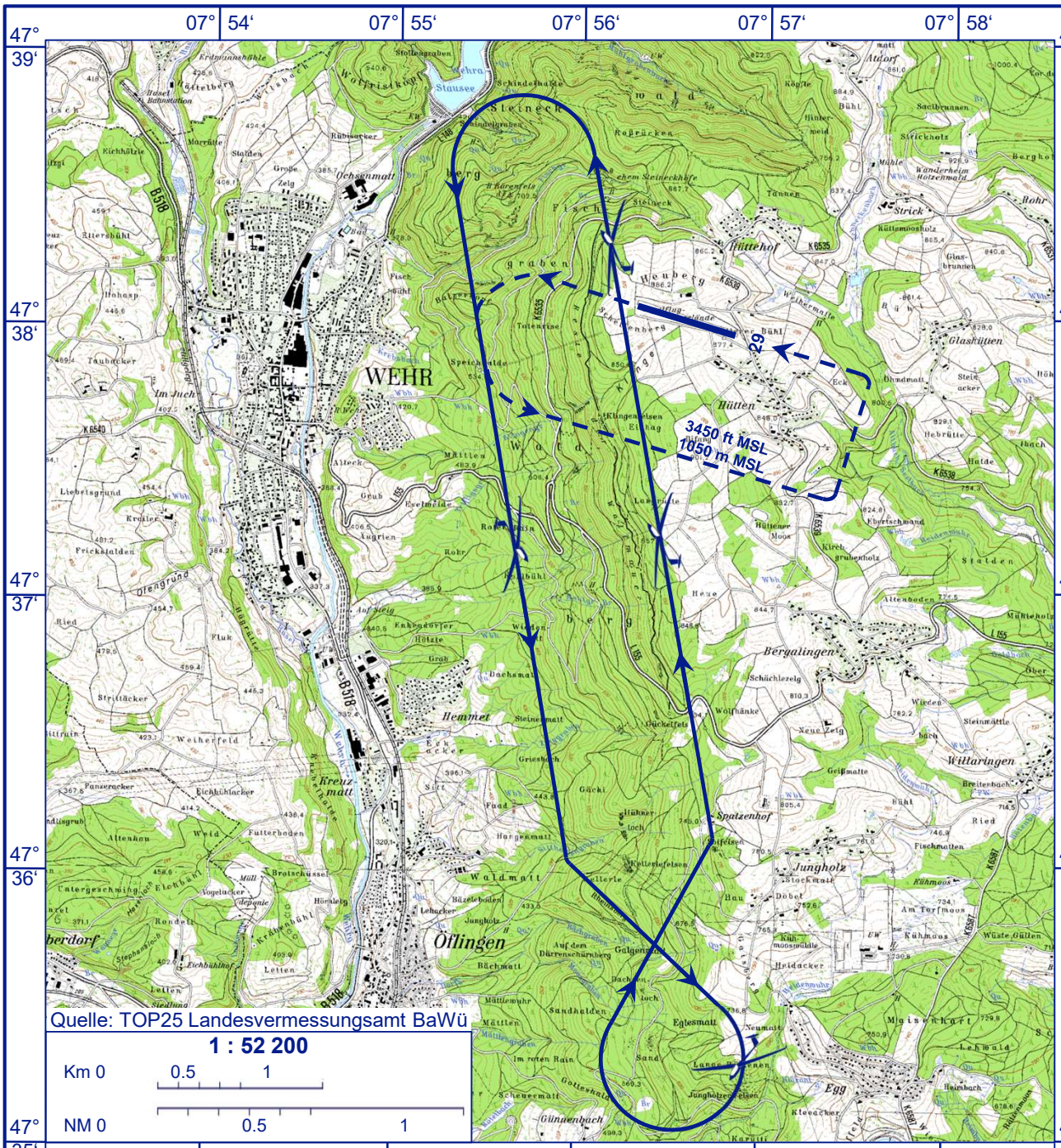

Quelle: TOP25 Landesvermessungsamt BaWü

1 : 52 200

Km 0 0.5 1

NM 0 0.5 1

Schematischer Querschnitt des Hangflugbereichs (nicht maßstäblich)
Schematic cross-section of hill soaring area (not scaled)

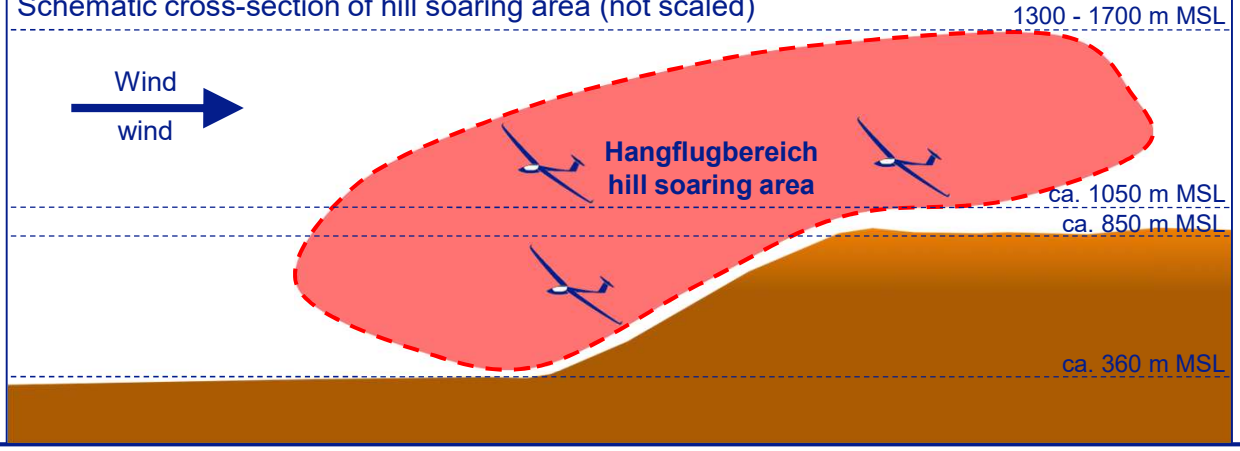

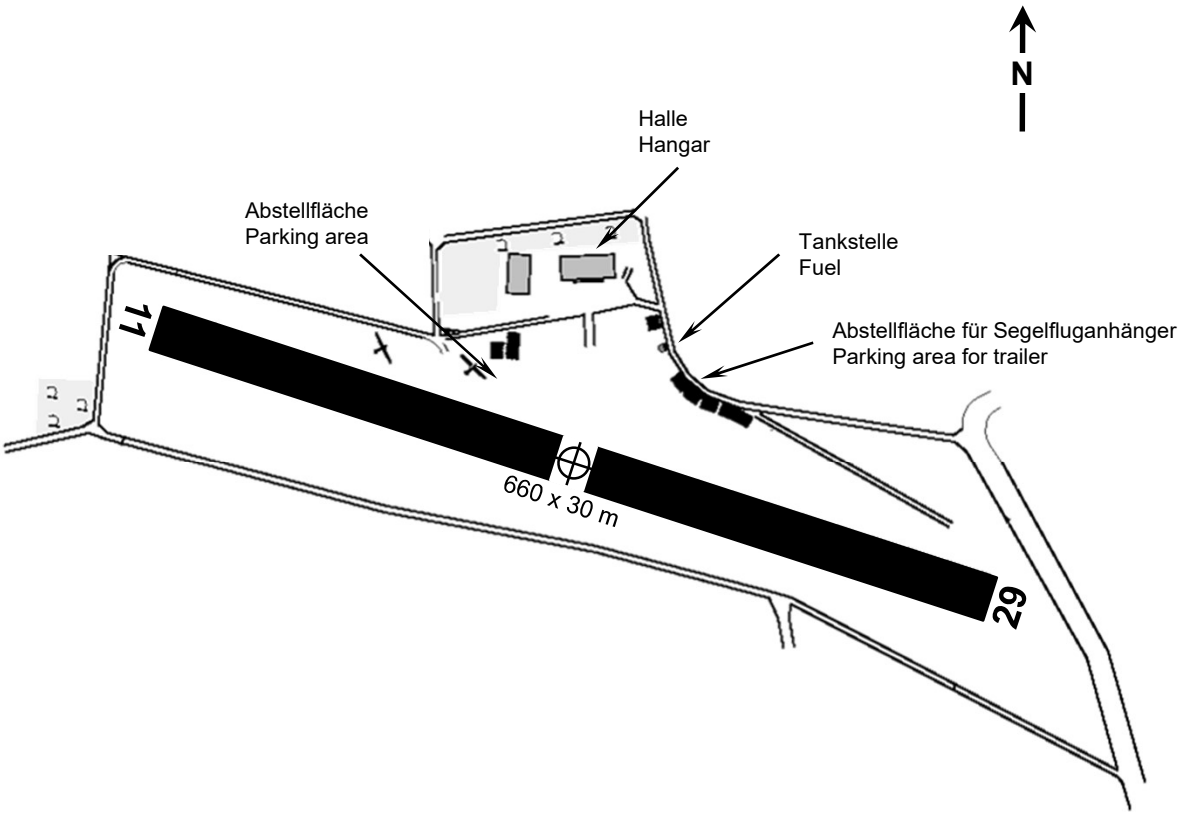

1 : 7 700

m 0 50 100 200

RWY	Dimensions	Surface	TORA	LDA
11	660 x 30 m	Grass	510 + 30 m	510 m
29			660 m	510 m

Evacuate RWY only to the north.

While parking keep the hangar exit clear.

Fuel only for club members.

Die RWY nur nach Norden verlassen.

Beim Abstellen die Hallenzufahrt freilassen.

Kraftstoff nur für Vereinsmitglieder.

© Luftsportgemeinschaft Hotzenwald e.V.